Semana da Mobilidade 2014
18 a 25 de Setembro

SEMANA DA MOBILIDADE 2014

CET www.cetsp.com.br SPTrans PREFEITURA DE SÃO PAULO TRANSPORTES

Mobilidade na Cidade de São Paulo

SEMANA DA MOBILIDADE 2014

CET www.cetsp.com.br SPTrans PREFEITURA DE SÃO PAULO TRANSPORTES

Frota de Veículos da Cidade* X População
Evolução ao longo do tempo
(Milhões)

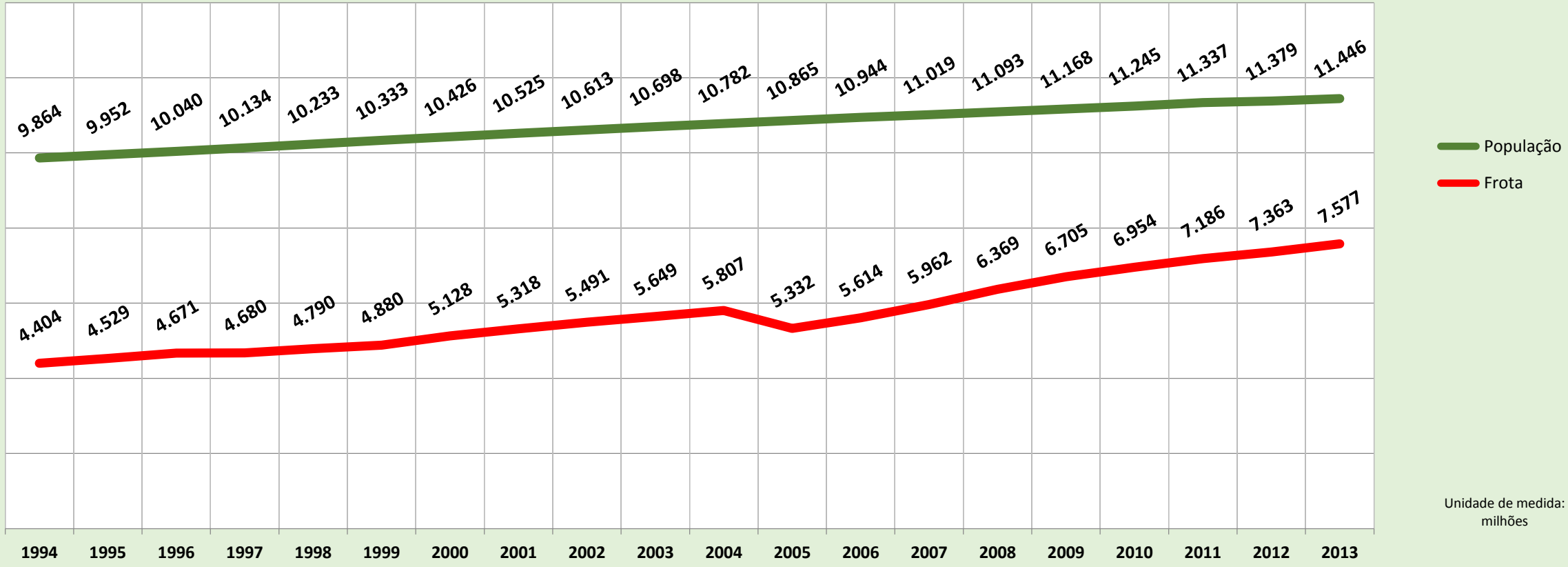

Unidade de medida: milhões

Fonte:CET
IBGE

*Frota da Cidade contempla todos os tipos de veículos motorizados

SEMANA DA MOBILIDADE 2014

CET www.cetsp.com.br SPTrans PREFEITURA DE SÃO PAULO TRANSPORTES

Índice de Mobilidade - Evolução

(população / total de viagens diárias realizadas = média de viagens diárias realizadas por pessoa)

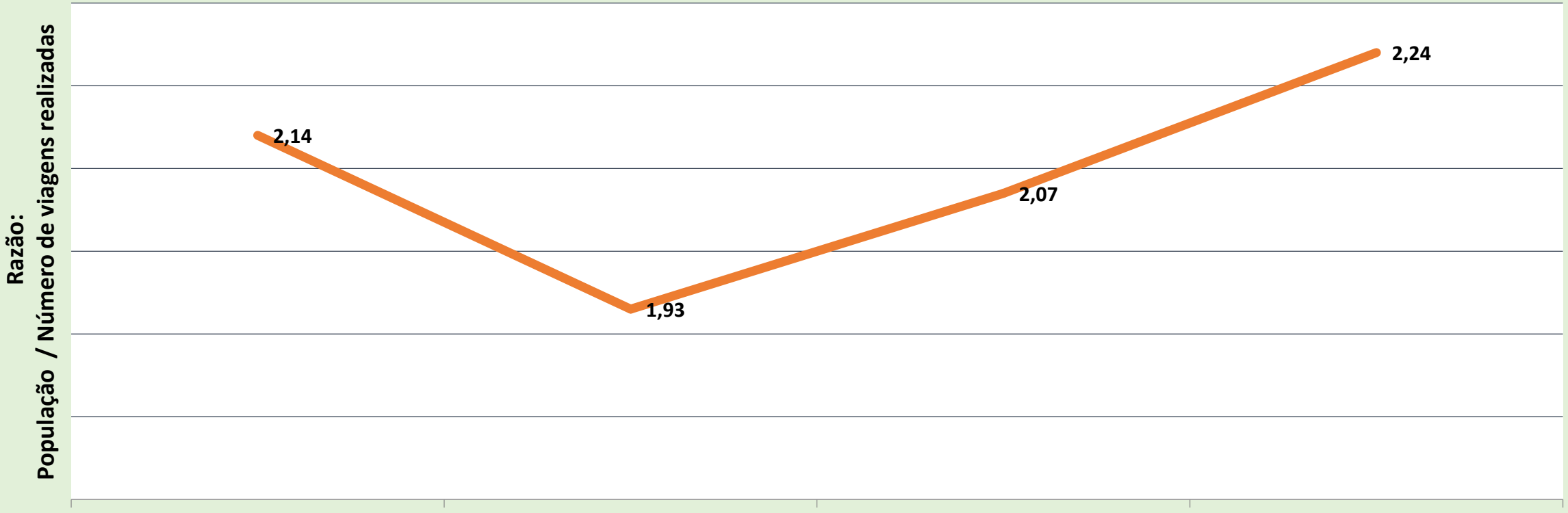

Fonte: Pesquisa
Origem **D**estino - Metrô

População 1987	Viagens diárias realizadas (todos os tipos de modais)
9.127.421	19.550.661

População 1997	Viagens diárias realizadas (todos os tipos de modais)
9.856.853	18.988.976

População 2007	Viagens diárias realizadas (todos os tipos de modais)
10.896.639	22.587.659

População 2012	Viagens diárias realizadas (todos os tipos de modais)
11.395.817	25.511.791

Evolução das viagens diárias por tipo de modal utilizado

(Milhões)

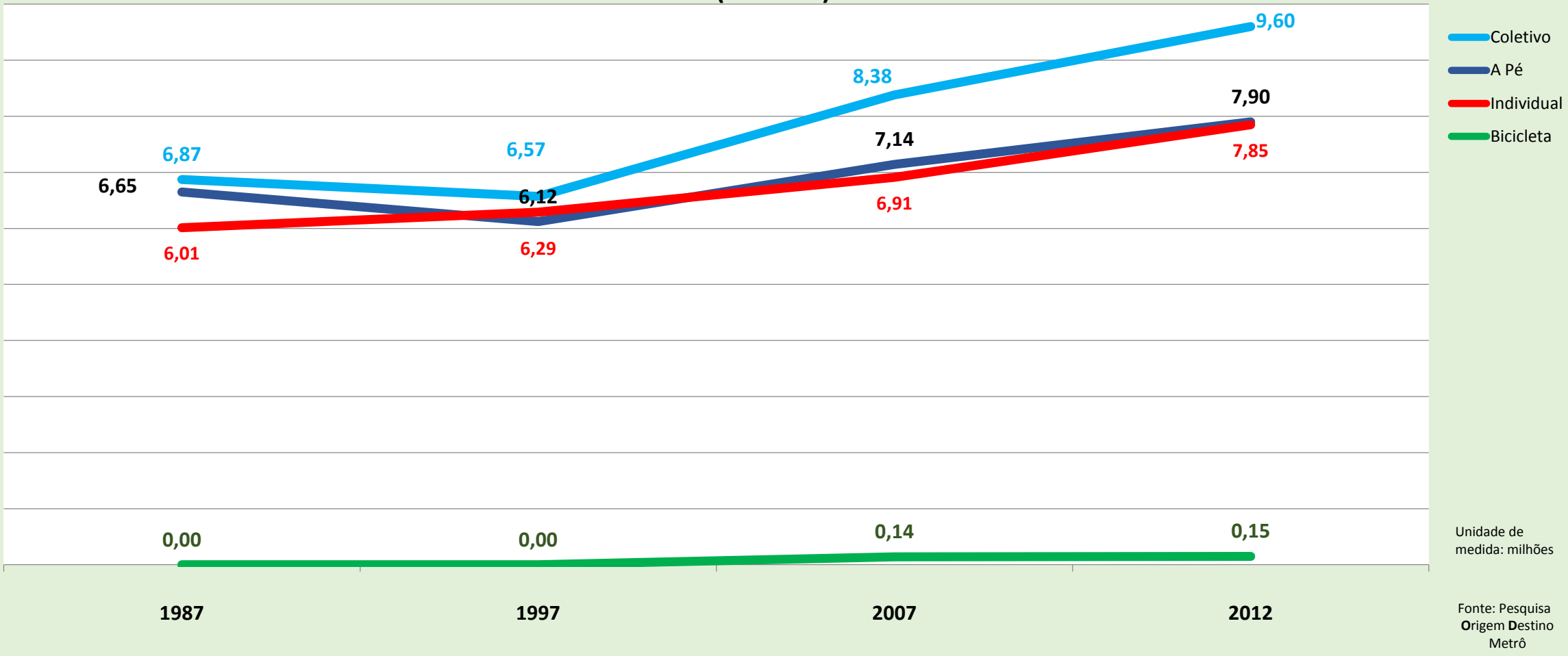

Unidade de medida: milhões

Fonte: Pesquisa **O**rigem **D**estino Metrô

SEMANA DA MOBILIDADE 2014

CET www.cetsp.com.br SPTrans PREFEITURA DE SÃO PAULO TRANSPORTES

Passageiros transportados por ano em Ônibus Coletivos (Bilhões)

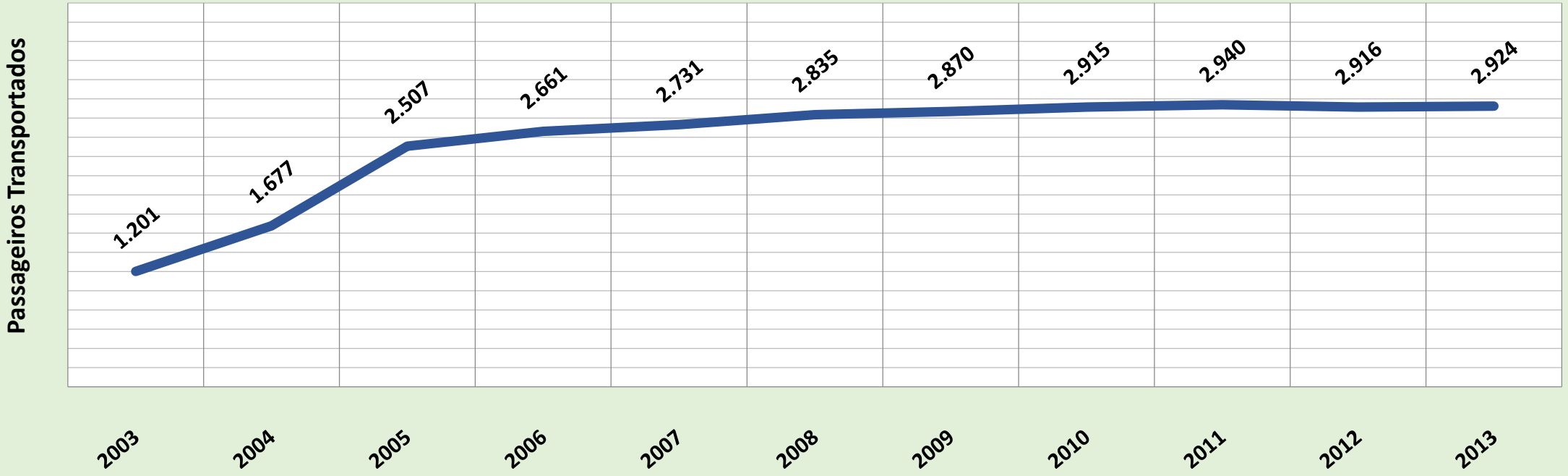

Unidade de medida: Bilhões

Fonte: SPTrans

Cenário 2014

Mais de **9 milhões de embarques/dia**, gerados por **4 milhões de usuários** de ônibus

Novas facilidades para aquisição de créditos de viagens, como **Bilhete Único Mensal,** com mais de **760 mil usuários** já cadastrados

Evolução da Frota de ônibus comum X Veículos com Acessibilidade

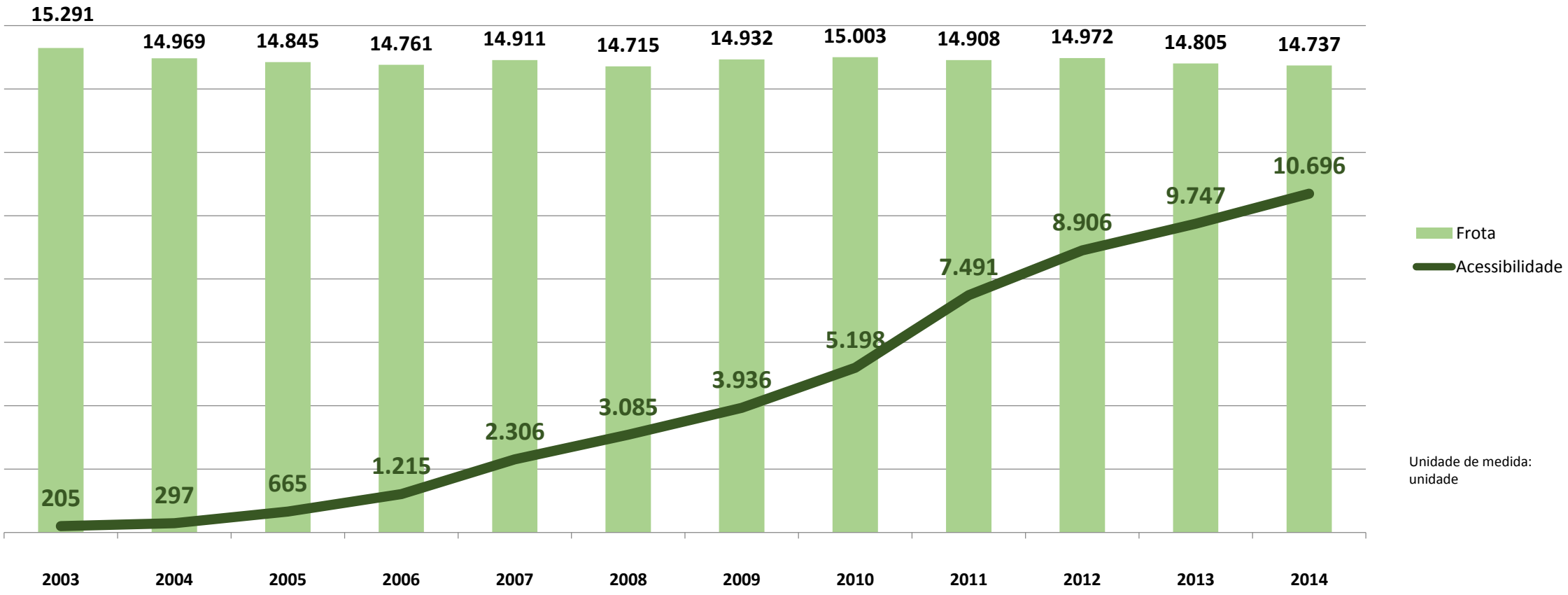

Unidade de medida: unidade

Veículos atendem às 1286 linhas de ônibus operadas na cidade

656 Veículos utilizam tecnologias sustentáveis (Ecofrota)

Fonte: SPTrans

Índice anual de Mortes / 100 mil habitantes

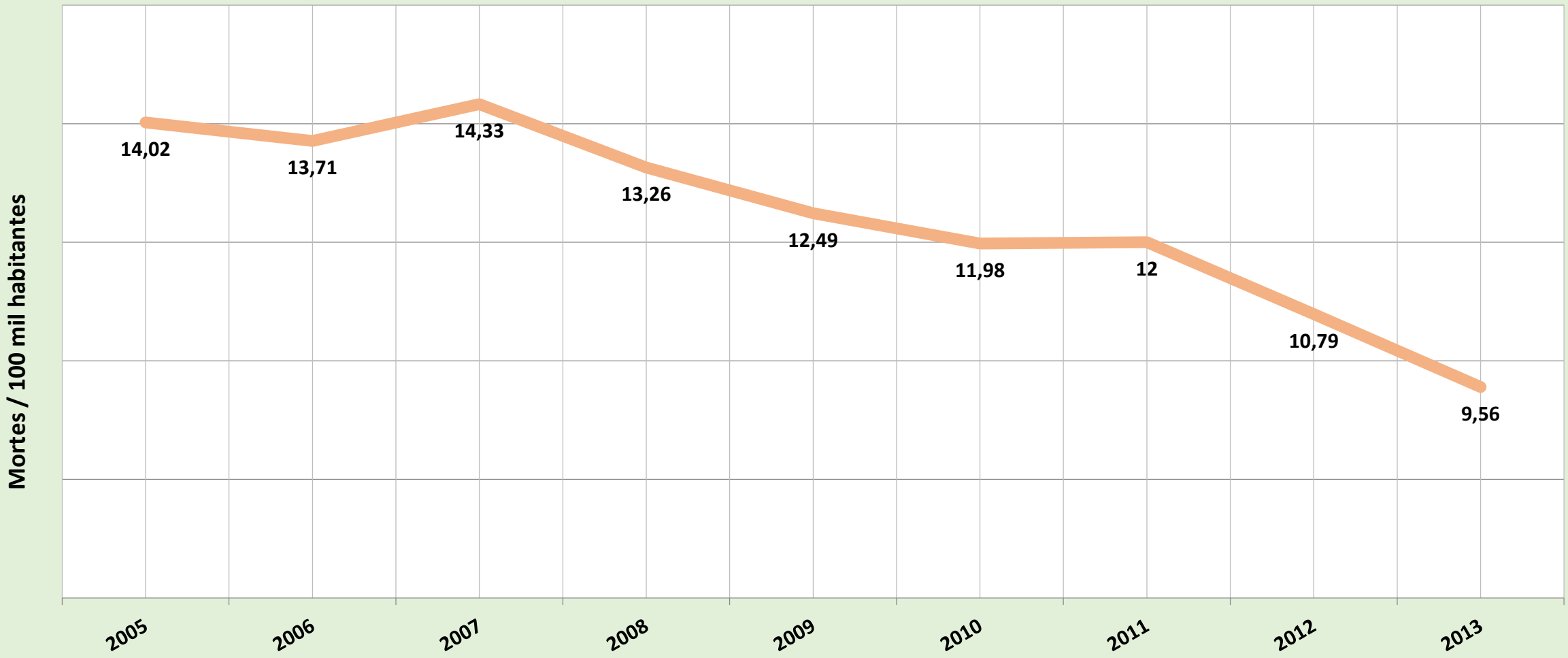

Fonte: DSP CET

Índices anuais de mortes por tipo de usuário
mortes/100.000 hab

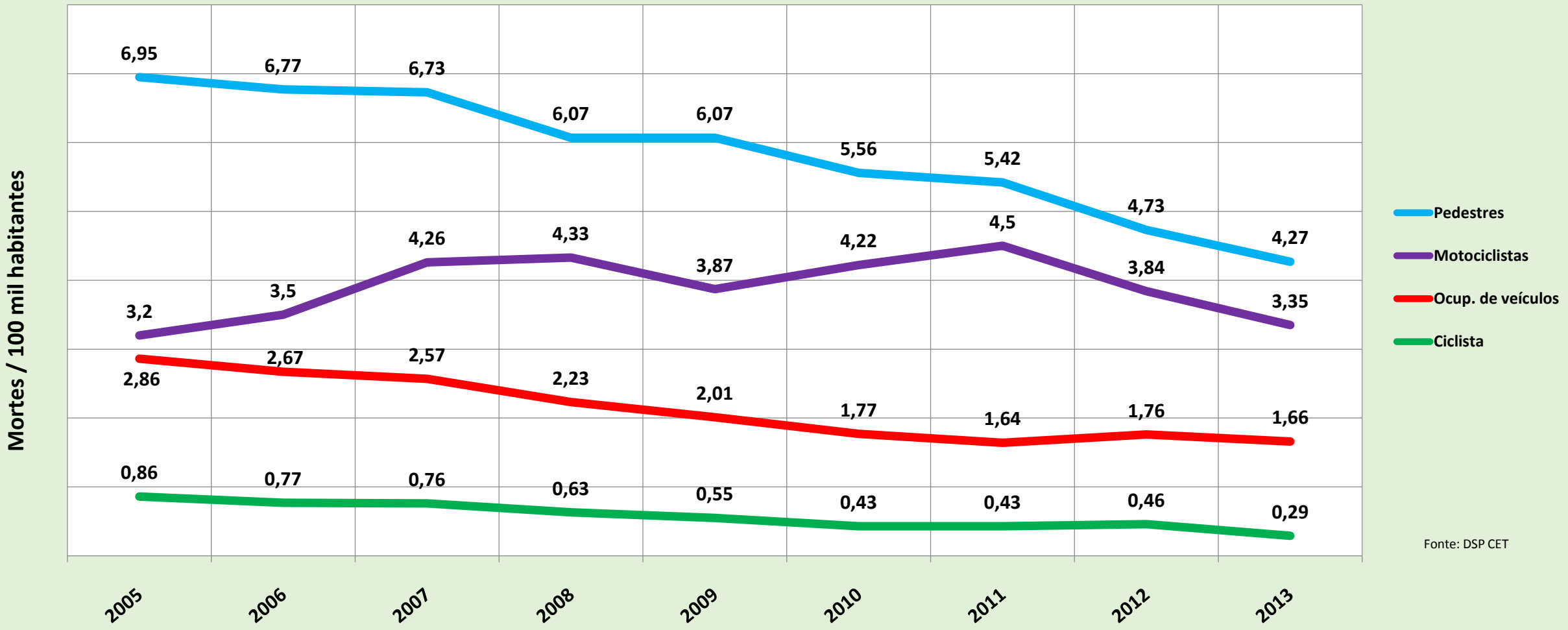

Fonte: DSP CET

Ações que resultaram em benefícios para pedestres e ciclistas 2013-2014

SEMANA DA MOBILIDADE 2014

CET www.cetsp.com.br SPTrans PREFEITURA DE SÃO PAULO TRANSPORTES

Benefícios para Pedestres e Ciclistas

Implantação da **ÁREA 40** visando reduzir a velocidade dos veículos em regiões de grande circulação de pedestres e ciclistas, evitando atropelamentos.

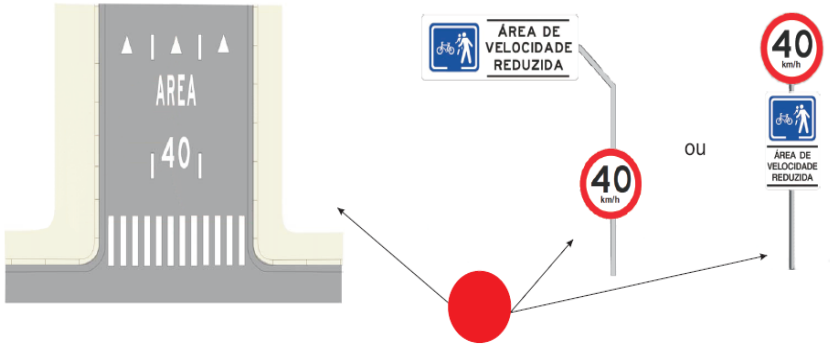

Já implantadas regiões Centro (contra rótula) e Lapa, totalizando 2,34 Km implantados dando andamento ao Compromisso Institucional, que tem como meta a implantação de 10 km até 2016

Fonte: GST CET



Benefícios para Pedestres

- Ampliação **do Programa de Proteção da Vida - PPV, contemplando AÇÕES PREVENTIVAS em 17 grandes avenidas e 11 locais com grande concentração de pedestres REDUZINDO EM 10% OS ATROPELAMENTOS,** dando prosseguimento ao cumprimento de 87,5 % do objetivo estipulado no Plano de metas. **15 ÁREAS** operadas por **408 ORIENTADORES DE TRAVESSIA**

Sinalização Implantada e existente:

- **4.395 TRAVESSIAS de PEDESTRES ILUMINADAS**
- **10.837 FAIXAS de PEDESTRES** pintadas e revitalizadas (além das já existentes na cidade)
- **16.566 SEMÁFOROS para PEDESTRES**, existentes na cidade

(Levantamento até 31Ago2014)

Fonte: SDE CET
SSI CET

Benefícios para Pedestres e Ciclistas

Programa CET no seu Bairro

Cuida da mobilidade no bairro, implantando a sinalização e desenvolvendo ações de orientação e educação de trânsito voltadas às escolas, associações de moradores e outras instituições.
O Programa é executado simultaneamente nas 7 regionais da CET, contemplando toda cidade. São escolhidos os locais com maior incidência de acidentes, levando em conta as demandas apresentadas pela população.

	Ações do Programa CET no seu Bairro	Total etapas 1 a 5 (17 fev a 01 ago) * Unidade
Sinalização	Travessia de Pedestres (Nova/Repintura)	3.190 *
	Áreas para embarque/desembarque de escolares	119
	Áreas para embarque/desembarque de ônibus	144
	Pintura de Lombadas	1.328 *
	Construção de Novas Lombadas	512 *
	Manutenção em Semáforos (Serviços Executados)	161 *
	Cruzamentos Semafóricos Revitalizados	161 *
	Semáforos novos implantados	4 *
	Revisões semafóricas	231 *
Educação	Ações voltadas para Educação de Trânsito (pessoas e instituições atendidas)	61.962

Fonte: GGE CET

Benefícios para Ciclistas

- Já implantados **70,68 km de CICLOVIAS ,** dando andamento ao Plano de Metas que tem como objetivo a implantação de 400 km até 2016

- Oferecimento do **CURSO "PEDALAR COM SEGURANÇA"** nas modalidades presencial e à distância com a finalidade de orientar o ciclista sobre os aspectos de segurança no trânsito ao pedalar, utilizando a bicicleta como meio de transporte, no exercício de atribuições profissionais ou em momentos de lazer.

- Implantação de **SINALIZAÇÃO VERTICAL, HORIZONTAL E SEMAFÓRICA** para orientação de ciclistas, dentre elas **112 semáforos** específicos para auxiliar na segurança durante a condução da bicicleta.

(Levantamento até 14Set2014)

Fonte: DCL CET
SSI CET
GED CET

Infraestrutura Cicloviária Existente na Cidade (Total 353, 99 Km)

Ciclovias	133,69 (63,01 até dez/13 + 70,68 até 14set/14)
Ciclofaixas	3,3
Ciclofaixa Operacional de Lazer	120,8
Rotas de Bicicletas	67,5
Ciclofaixa de Lazer Periódica	24,2
Calçada Compartilhada	4,5

Até 14set2014
Fonte: CET- DCL

4.505 vagas em bicicletários e paraciclos

integrados às estações da CPTM e do Metrô, e aos terminais da SPTrans

Biclicletários em Terminais de Ônibus
Terminal
Campo Limpo
Grajaú
Guarapiranga
V.N. Cachoeirinha
Pinheiros
Pirituba
Santo Amaro
Sapopemba
Varginha
Mercado (Expr. Tiradentes)
Sacomã (Expr. Tiradentes)

Biclicletários no Expresso Tiradentes
Estação
Pedro II
Ana Neri
Alberto Lion
Clube Atlético Ypiranga
Nossa Senhora Aparecida
Rua do Grito

- Disponibilização de **180 ESTAÇÕES de ALUGUEL DE BICICLETAS** em parceria com os programas **BikeSampa e CicloSampa e Implantação do Bicicletário Público do Largo de Pinheiros**