AVALIAÇÃO DA REDE CICLOVIÁRIA

CONSELHO MUNICIPAL DE TRANSPORTE E TRÂNSITO

Junho/2017

Companhia de Engenharia de Tráfego

PREFEITURA DE SÃO PAULO
MOBILIDADE E TRANSPORTES

REDE CICLOVIÁRIA

SISTEMA CICLOVIÁRIO

PLANO DE MOBILIDADE

SISTEMA CICLOVIÁRIO

EDUCAÇÃO E MOBILIZAÇÃO SOCIAL

- REDE ESTRUTURAL CICLOVIÁRIA
- SISTEMA DE BICICLETAS COMPARTILHADAS
- ESTACIONAMENTO DE BICICLETAS

COMUNICAÇÃO E OUTRAS AÇÕES

LEGISLAÇÃO

Estabelece OBJETIVOS, DIRETRIZES, METAS E AÇÕES

POLÍTICA NACIONAL DE MOBILIDADE URBANA + **PLANO DE MOBILIDADE** + **PLANO DIRETOR ESTRATÉGICO**



A implantação das estruturas cicloviárias é parte integrante da Política de Mobilidade do Município, e busca a efetivação dos princípios da :

- **Política Nacional de Mobilidade Urbana (Lei Federal 12.587, de 2012)**
- **Plano Diretor Estratégico (Lei Municipal 16.050, de 2014) no Município de São Paulo.**
- **Plano de Mobilidade (DECRETO Nº 56.834, DE 24 DE FEVEREIRO DE 2016)**

Compete ao órgão com circunscrição sobre a via planejar, projetar, regulamentar e operar o trânsito de veículos, de pedestres e de animais, e promover o desenvolvimento da circulação e da segurança de ciclistas, artigo 24, inciso II da Lei n° 9503/1997 (Código de Trânsito Brasileiro)

AVALIAÇÃO DA REDE CICLOVIÁRIA

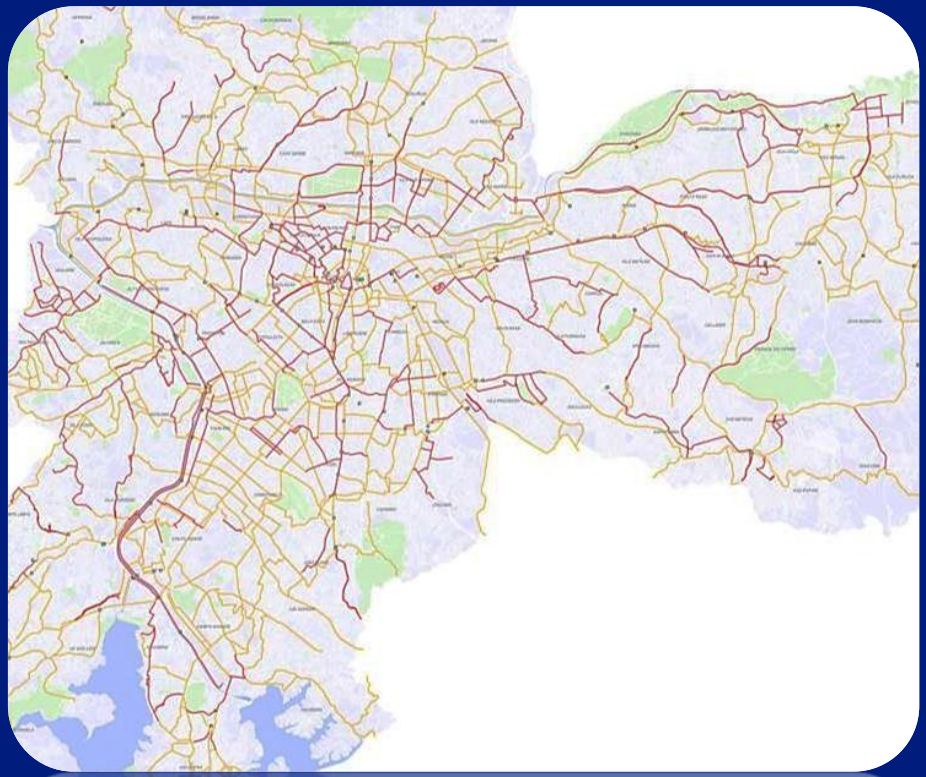

OBJETIVO:

- Qualificar estruturas cicloviárias existentes;
- Referenciar alterações para consolidar Rede Cicloviária Estrutrural na cidade;
- Referenciar novas implantações

AVALIAÇÃO DOS PADRÕES DE PROJETOS DAS ESTRUTURAS CICLOVIÁRIAS

CICLOVIA

Pista de uso exclusivo de bicicletas e outros ciclos, com segregação física do tráfego lindeiro motorizado ou não motorizado, com sinalização viária, podendo ter piso diferenciado no mesmo plano da pista de rolamento ou no nível da calçada.

•Ciclovia unidirecional: é a ciclovia com um único sentido de circulação.

• Ciclovia bidirecional: é a ciclovia com sentido duplo de circulação.

CICLOFAIXA

Faixa de rolamento de uso exclusivo à circulação de ciclos, com segregação visual do tráfego lindeiro, podendo ter piso diferenciado no mesmo plano da pista de rolamento.

• Ciclofaixa unidirecional: é a ciclofaixa com um único sentido de circulação.

• Ciclofaixa bidirecional: é a ciclofaixa com sentido duplo de circulação.

CICLORROTA

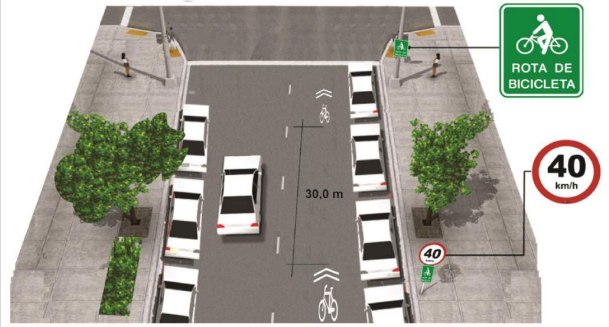

Sinalização cicloviária específica em pista de rolamento compartilhada com os demais veículos, onde as características de volume e velocidade do trânsito na via possibilitam o uso de vários modos de transporte a necessidade de segregação. Este conceito deve ser aplicado obedecendo ao princípio da continuidade e orientação, especialmente em complementação às ciclovias e ciclofaixas.

CALÇADAS COMPARTILHADAS

• Calçada Compartilhada: espaço comum para a circulação de bicicletas, pedestres e cadeirantes, devidamente sinalizado.

CALÇADAS PARTILHADAS

• Calçada Partilhada: espaço exclusivo para circulação de ciclos sobre a calçada, com segregação visual do tráfego de pedestres, podendo ter piso diferenciado no mesmo plano, devidamente sinalizado. As calçadas partilhadas equiparam-se às ciclofaixas, porém na calçada.

O CTB (Art. 59) prevê que a circulação de bicicletas nas calçadas é permitida "desde que autorizada e devidamente sinalizada pelo órgão ou entidade com circunscrição sobre a via". Sem que haja prejuízo do conforto e da segurança de pedestres e cadeirantes, é possível utilizar as calçadas de duas formas na rede cicloviária:

CICLOVIAS / CICLOFAIXAS

PLACAS DE ORIENTAÇÃO

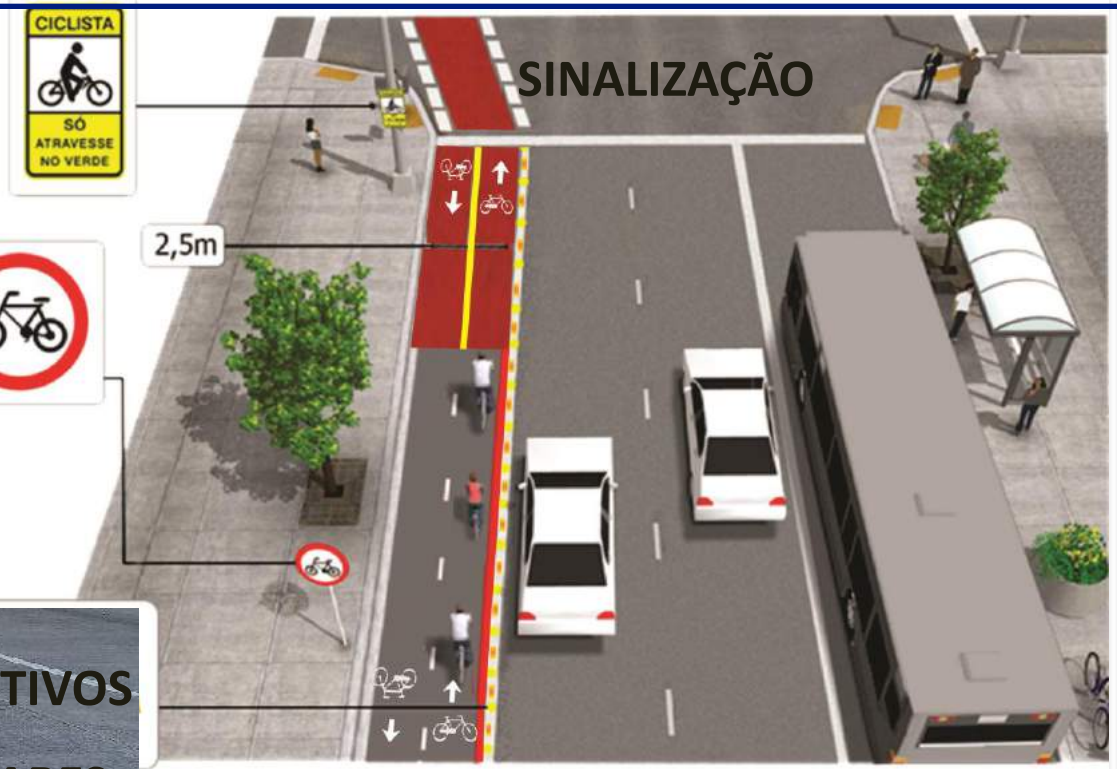

DISPOSITIVOS AUXILIARES

AJUSTES GEOMÉTRICOS

SINALIZAÇÃO

EM AVALIAÇÃO

GRADIS

ESTACIONAMENTO

CICLORROTAS

EM AVALIAÇÃO

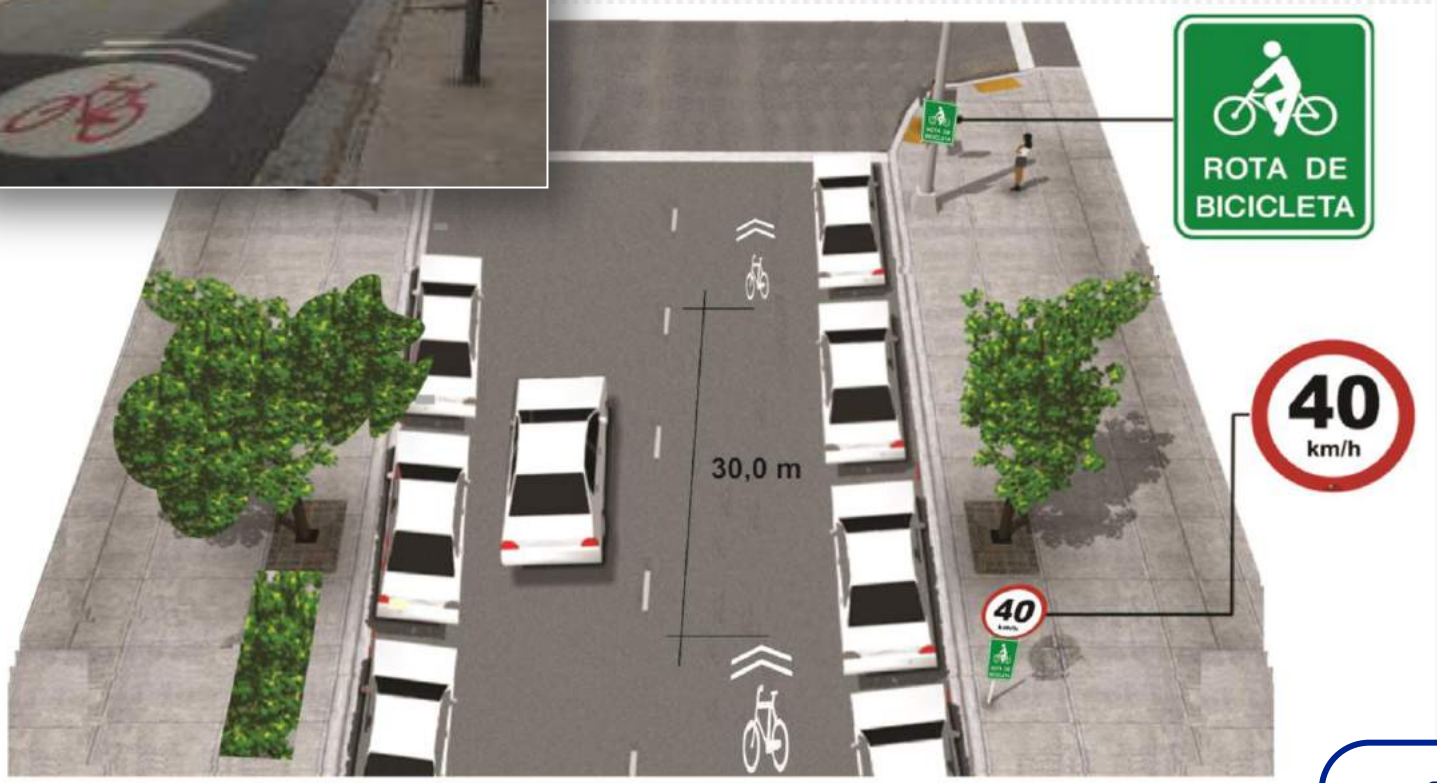

AVALIAÇÃO DOS TRAJETOS

AVALIAÇÃO DA REDE CICLOVIÁRIA



DIRETRIZES PARA AVALIAÇÃO DE TRAJETOS

– REDE CICLOVIÁRIA DEVE APRESENTAR:

- CONECTIVIDADE
- LIGAÇÕES PERIMETRAIS E RADIAIS
- LINEARIDADE
- INTERMODALIDADE
- FUNCIONALIDADE RELATIVA AO USO DO SOLO
- FUNCIONALIDADE RELATIVA À HIERARQUIA VIÁRIA

MATRIZ DE AVALIAÇÃO

Definição dos parâmetros:

1. Conectividade
2. Atratividade no eixo
3. Demandas sociais
4. Segurança na circulação
5. Análise de alternativas

CONECTIVIDADE

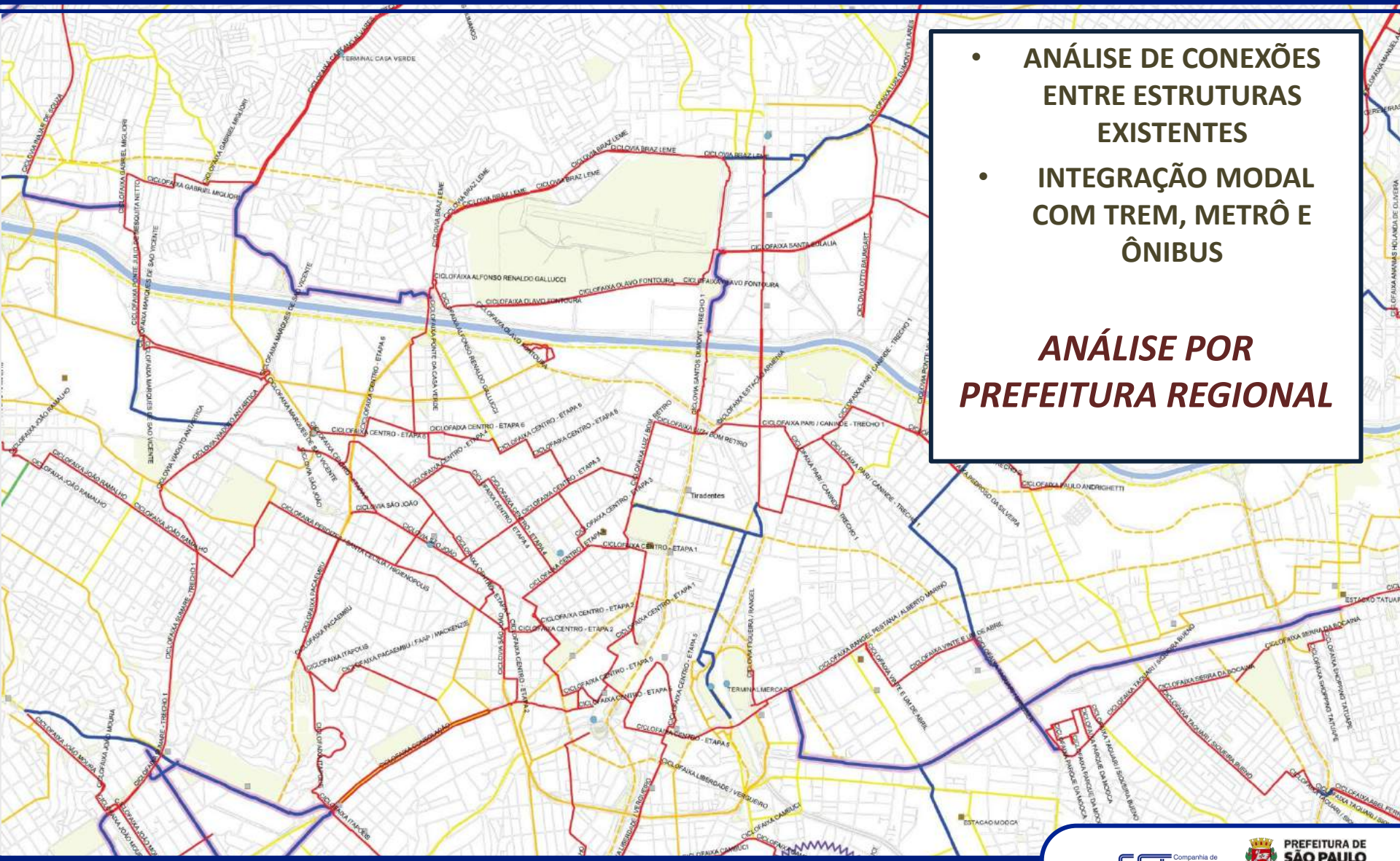

- ANÁLISE DE CONEXÕES ENTRE ESTRUTURAS EXISTENTES
- INTEGRAÇÃO MODAL COM TREM, METRÔ E ÔNIBUS

ANÁLISE POR PREFEITURA REGIONAL

ATRATIVIDADE NO EIXO

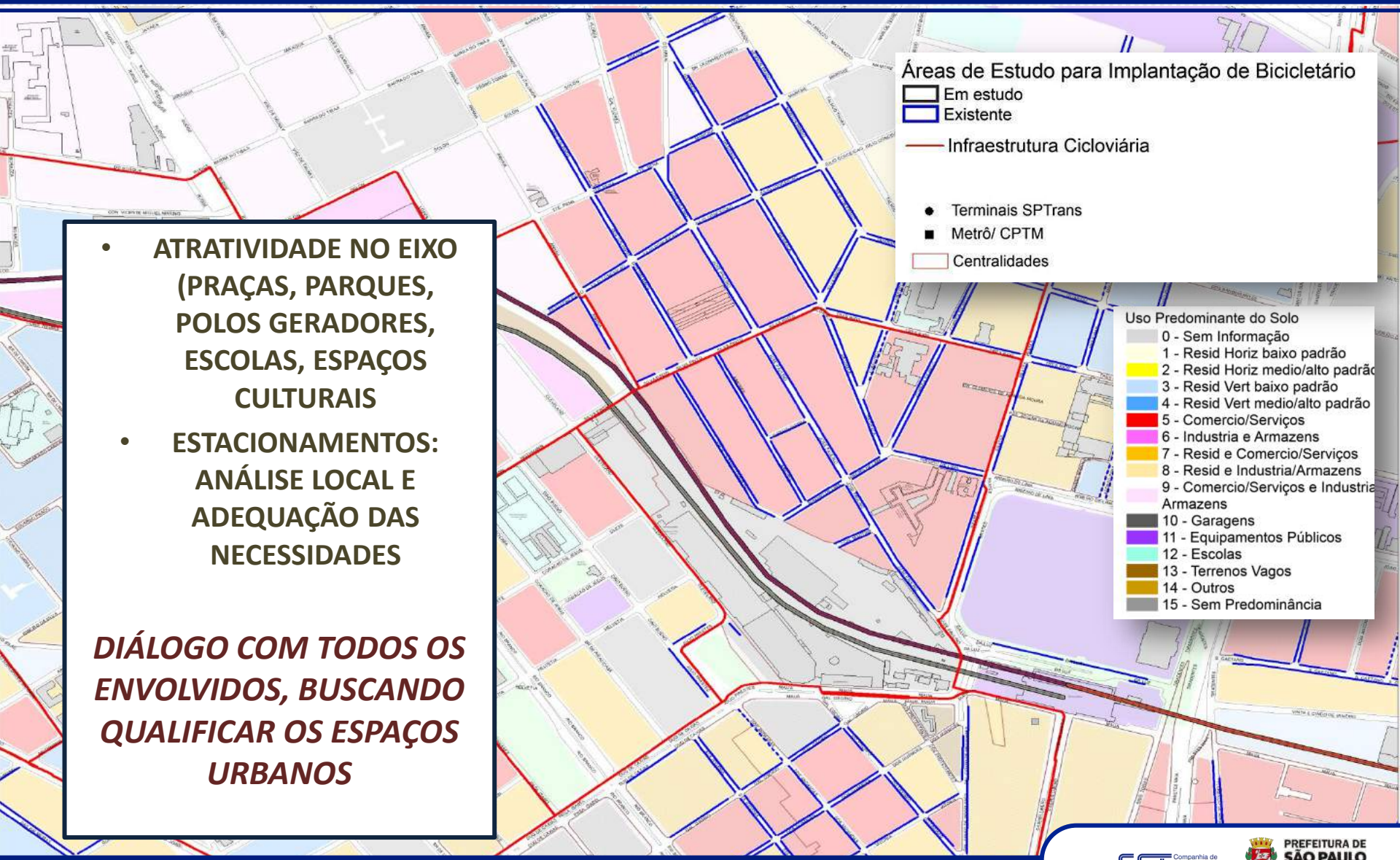

- **ATRATIVIDADE NO EIXO (PRAÇAS, PARQUES, POLOS GERADORES, ESCOLAS, ESPAÇOS CULTURAIS**
- **ESTACIONAMENTOS: ANÁLISE LOCAL E ADEQUAÇÃO DAS NECESSIDADES**

DIÁLOGO COM TODOS OS ENVOLVIDOS, BUSCANDO QUALIFICAR OS ESPAÇOS URBANOS

DEMANDAS SOCIAIS

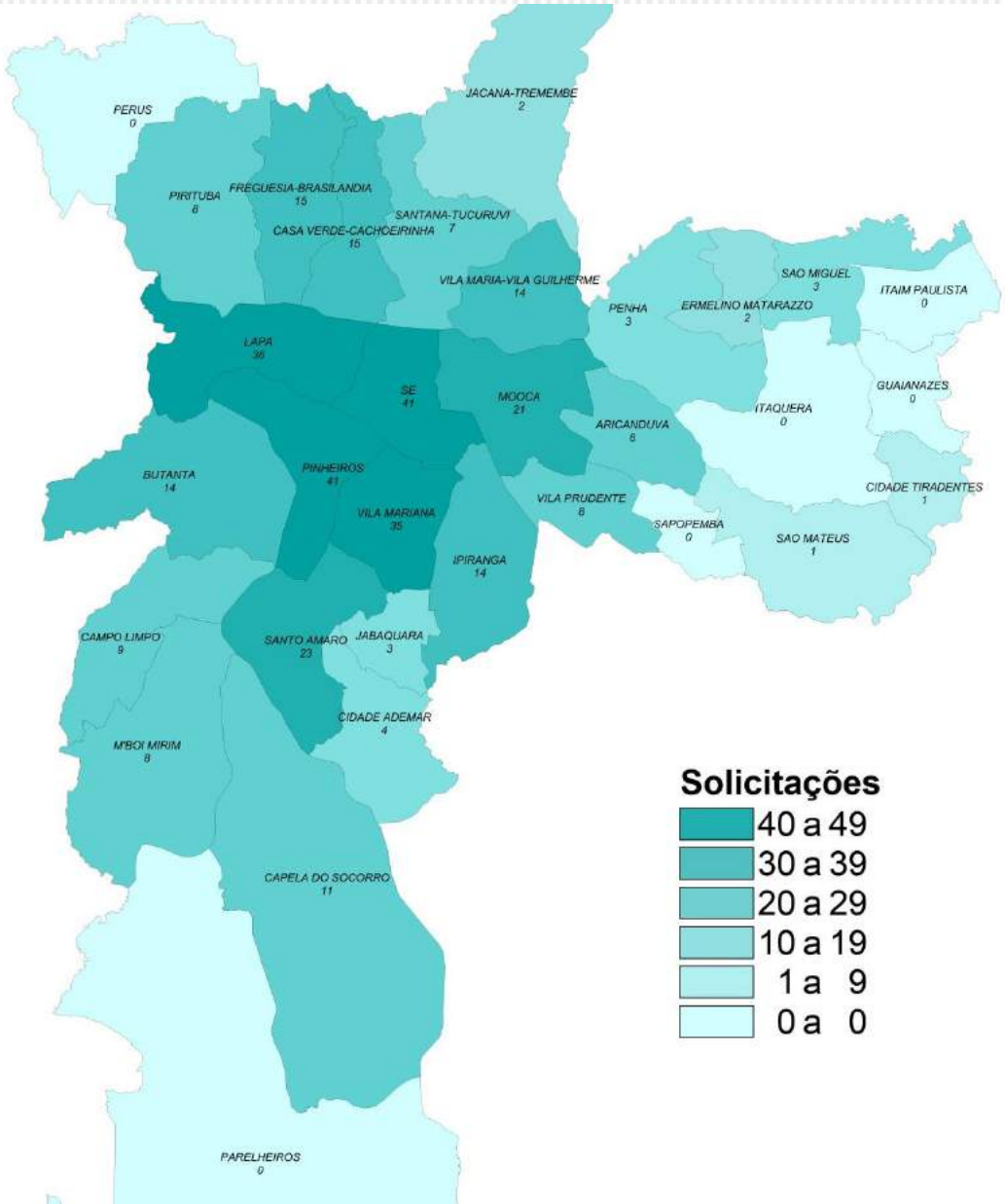

SOLICITAÇÕES:

- **CÂMARA TEMÁTICA DE BICICLETAS**
- **CÂMARA MUNICIPAL**
- **ASSEMBLEIA LEGISLATIVA**
- **ASSOCIAÇÕES**
- **MUNÍCIPES**

355 SOLICITAÇÕES DE IMPLANTAÇÃO, RETIRADA, MANUTENÇÃO E AVALIAÇÃO DE INFRAESTRUTURA CICLOVIÁRIA

SEGURANÇA NA CIRCULAÇÃO

AVALIAÇÃO

- SINALIZAÇÃO HORIZONTAL
- SINALIZAÇÃO VERTICAL
- SINALIZAÇÃO SEMAFÓRICA
- OUTRAS INTERFERÊNCIAS QUE POSSAM GERAR RISCO

PROPOSTAS DE MELHORIAS PARA A CONDIÇÃO DE CIRCULAÇÃO DOS CICLISTAS

ANÁLISE DE ÁREA

BOM RETIRO

BOM RETIRO
Contexto Geral

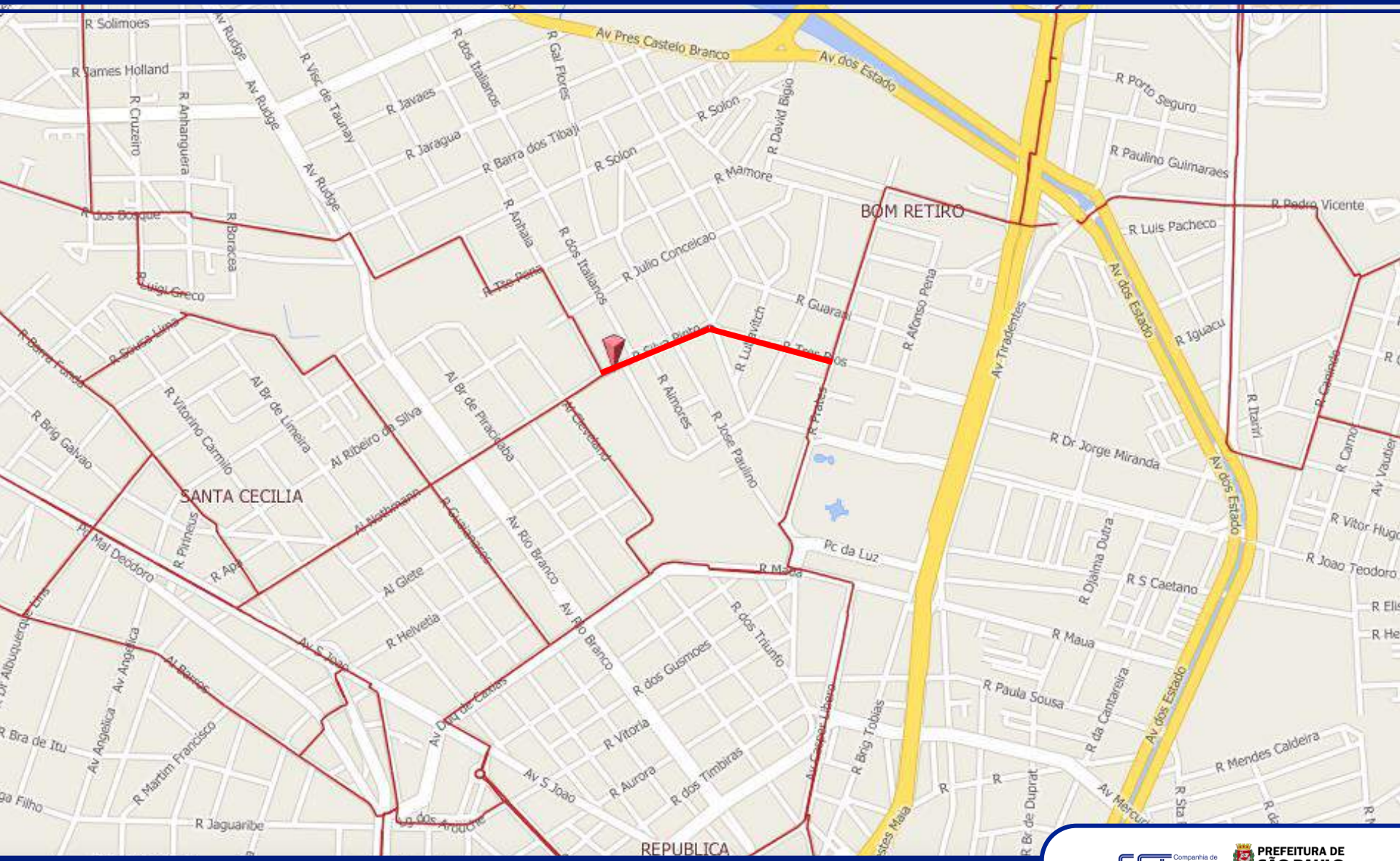

http://cetsp1.cetsp.com.br/mapabasico/map.aspx?map=infraciclo

BOM RETIRO
Contexto Local

BOM RETIRO
Zona Azul

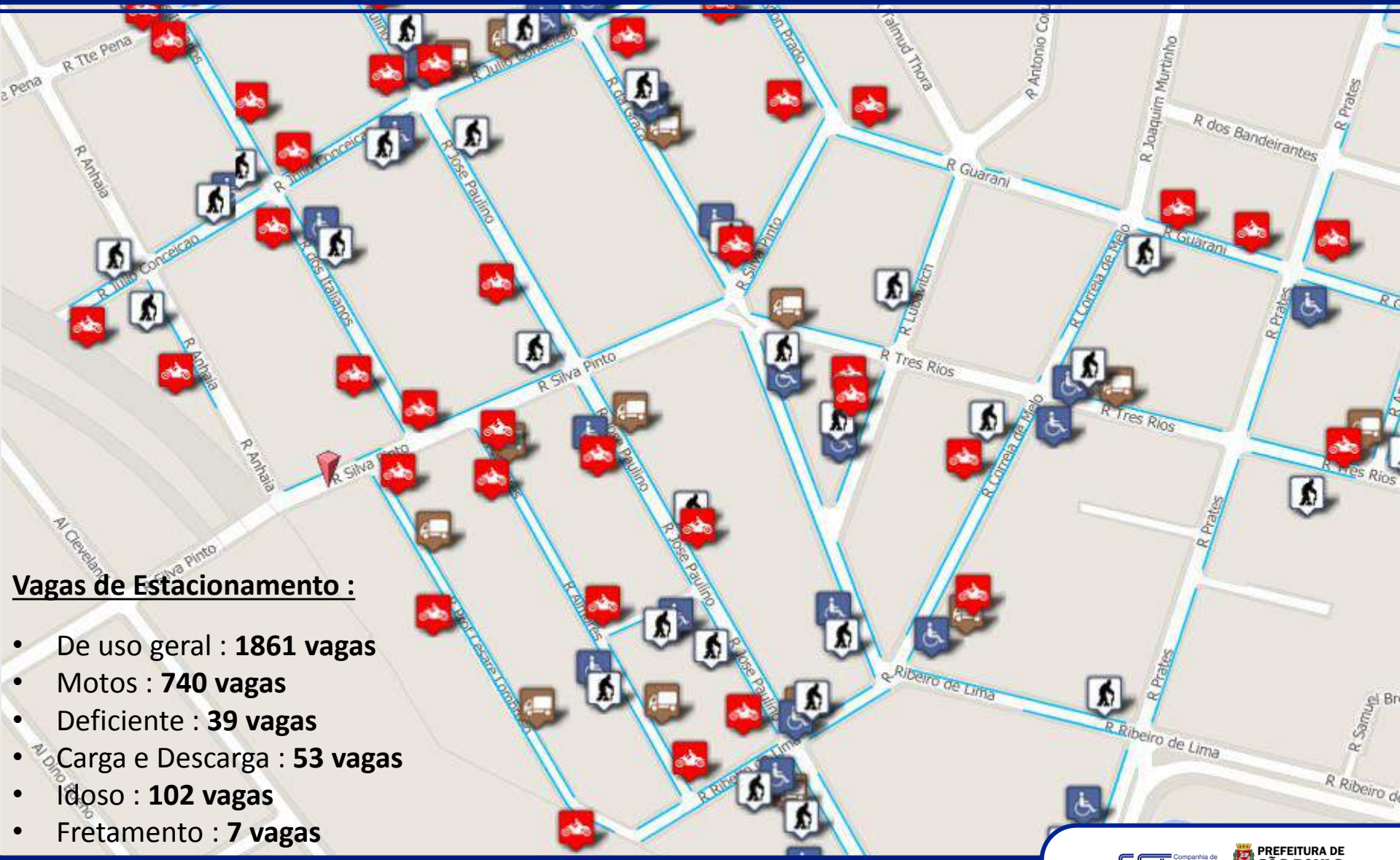

Vagas de Estacionamento :

- De uso geral : **1861 vagas**
- Motos : **740 vagas**
- Deficiente : **39 vagas**
- Carga e Descarga : **53 vagas**
- Idoso : **102 vagas**
- Fretamento : **7 vagas**

http://cetsp1.cetsp.com.br/mapabasico/map.aspx?map=zonaazul (ZONA Prates e José Paulino)

BOM RETIRO
Zona Azul

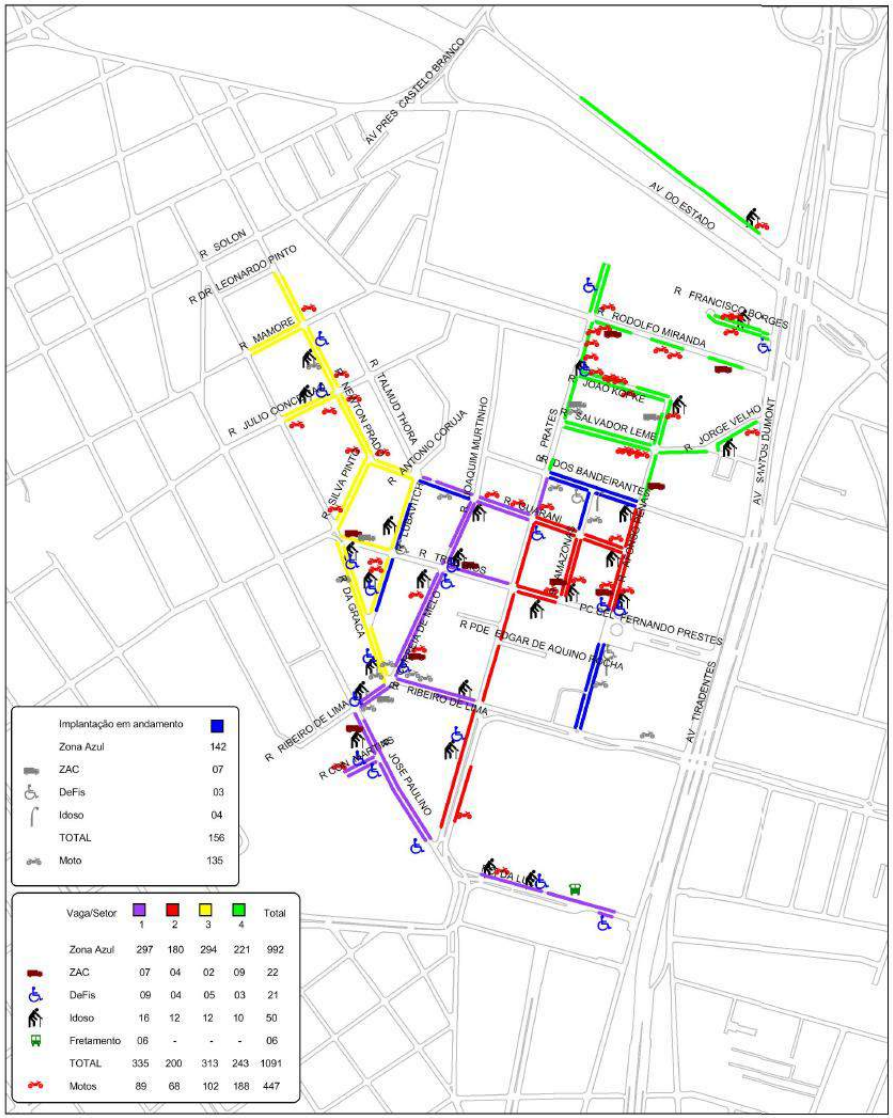

Vaga/Setor	1	2	3	4	Total
Zona Azul	297	180	294	221	992
ZAC	07	04	02	09	22
DeFis	09	04	05	03	21
Idoso	16	12	12	10	50
Fretamento	06	-	-	-	06
TOTAL	335	200	313	243	1091
Motos	89	68	102	188	447

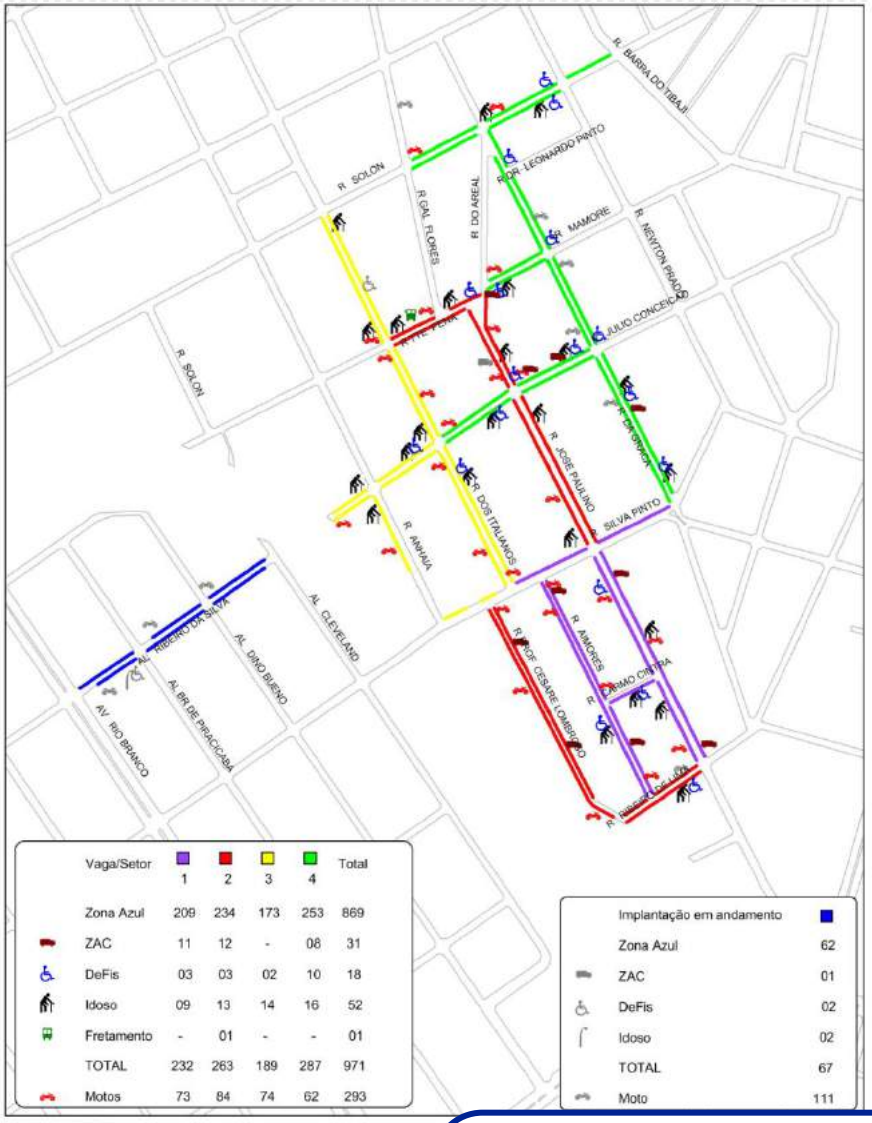

Vaga/Setor	1	2	3	4	Total
Zona Azul	209	234	173	253	869
ZAC	11	12	-	08	31
DeFis	03	03	02	10	18
Idoso	09	13	14	16	52
Fretamento	-	01	-	-	01
TOTAL	232	263	189	287	971
Motos	73	84	74	62	293

Implantação em andamento	
Zona Azul	62
ZAC	01
DeFis	02
Idoso	02
TOTAL	67
Moto	111

BOM RETIRO
Contexto na Rua Três Rios

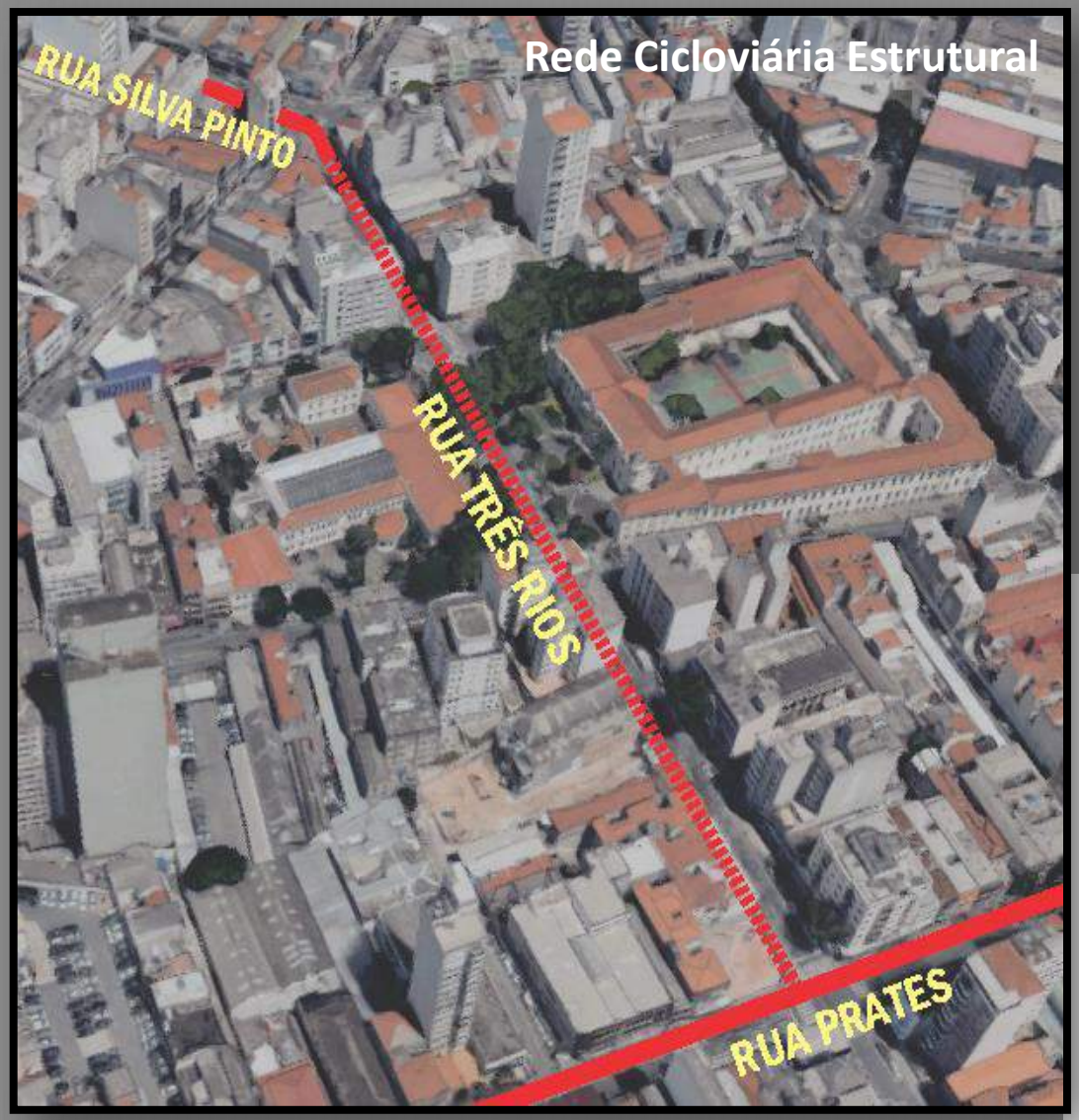

ANÁLISE ATUAL DA VIA:

Trecho entre Rua da Silva Pinto e Rua Prates
Extensão do trecho : **320 m**
Zona Azul : **27 vagas**
Taxi : **Não há**
Motos : **Não há**
Deficiente : **Não há**
Idoso : **não há**
Carga e Descarga : **4 vagas**
Faixas Veículares : **2**
Ônibus: **4 linhas**
Ponto de Ônibus : **01**

NÃO HÁ POSSIBILIDADE DE IMPLANTAR ESTACIONAMENTO EM AMBOS LADO DA VIA

BOM RETIRO
Contexto na Rua Silva Pinto

ANÁLISE ATUAL DA VIA :

Trecho entre Rua da Graça e Rua Anhaia
Extensão do trecho : **320 m**
Zona Azul : **34 vagas**
Taxi : **03 vagas**
Motos : **Não há**
Deficiente : **Não há**
Carga e Descarga : **Não há.**
Faixas Veículares : **2** (não houve perdas)
Ônibus: **6 linhas**
Ponto de Ônibus : **01**

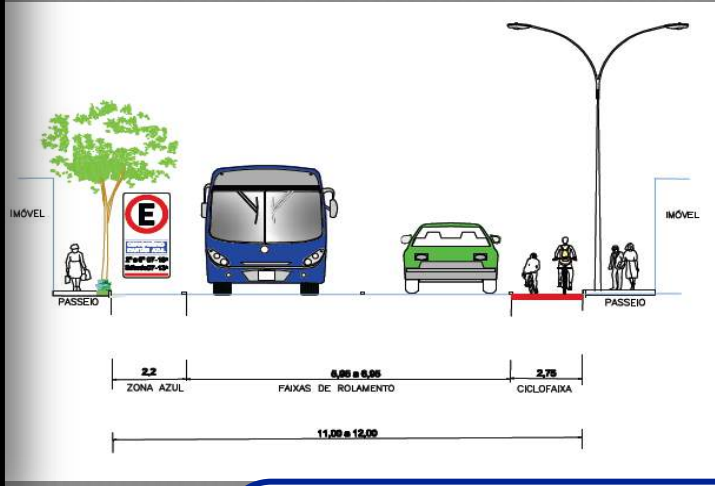

BOM RETIRO

Corte Esquemático - proposta

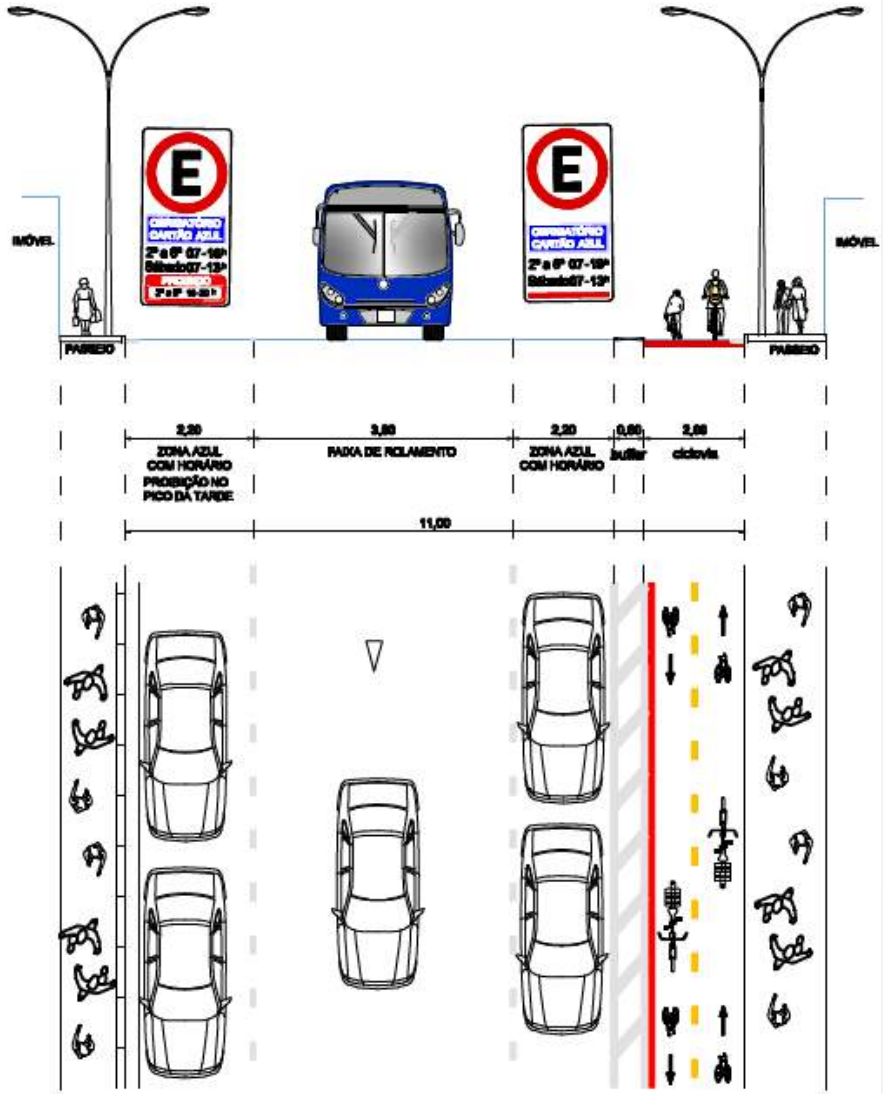

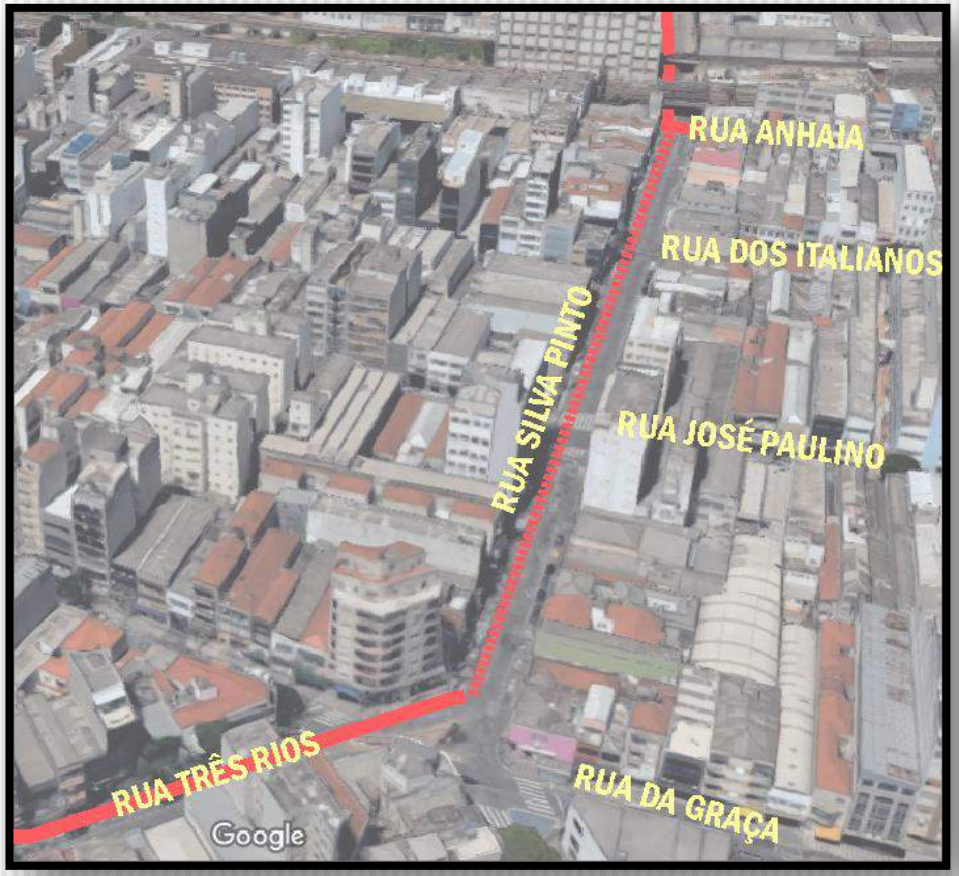

BOM RETIRO
Proposta

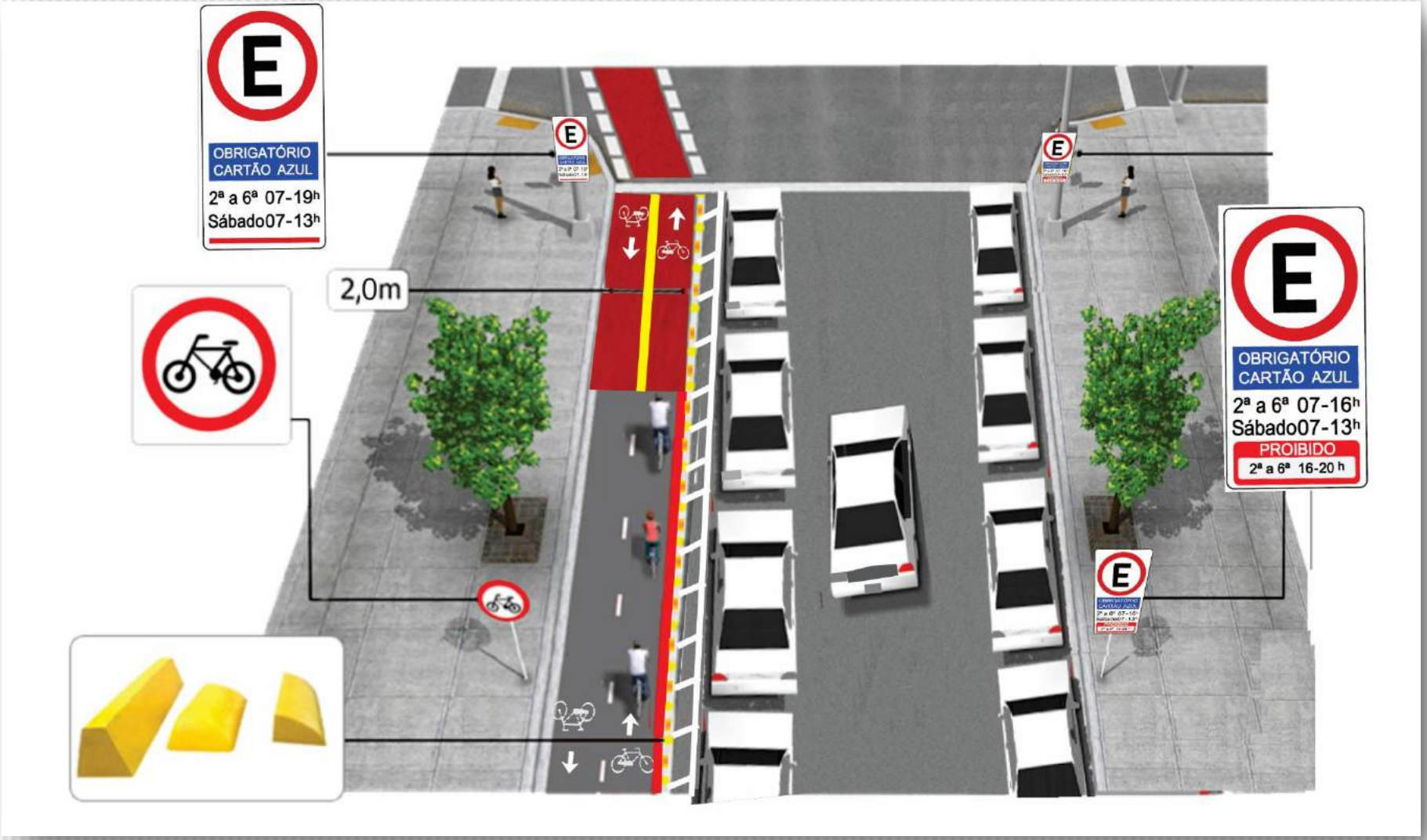

Companhia de Engenharia de Tráfego

DIRETORIA DE PLANEJAMENTO
SUPERINTENDÊNCIA DE PLANEJAMENTO
GERÊNCIA DE PLANEJAMENTO
CET DPM - Departamento de Planejamento de Modos Ativos

PREFEITURA DE SÃO PAULO
TRANSPORTES